Oefa

Organismo
de Evaluación
y Fiscalización
Ambiental

Organismo de Evaluación y Fiscalización Ambiental

DOCUMENTO PRELIMINAR

MANUAL DE USUARIO PARA EL REGISTRO DE RESULTADOS DE MONITOREO AMBIENTAL EN LA PLATAFORMA ÚNICA DE SERVICIOS DIGITALES- PLUSD

ADMINISTRADOS

Introducción

¿QUÉ CONTIENE ESTE MANUAL DE USUARIO?

Este manual contiene la descripción e indicación de cómo se debe de realizar el registro correspondiente a los documentos, equipos ambientales, informes de ensayo y resultados de monitoreos, el cual el administrado realiza de acuerdo a lo indicado en su Instrumento de Gestión Ambiental.

ADMINISTRADOS

- ✓ Permite contar con información integrada, sistematizada y actualizada.
- ✓ Permite acceder a información de consulta resultados de monitoreo ambiental.
- ✓ Fomentamos el cumplimiento de las obligaciones ambientales.

FUNCIONALIDAD

DOCUMENTO PRELIMINAR

Ingreso a la Plataforma

1 Ingresar a la Plataforma Única de Servicios Digitales- PLUSD

Link: https://calidad.oefa.gob.pe/plusd

2 Ingresar las credenciales en el formulario del Login y seleccionar el botón Ingresar, se recomienda cambiar la contraseña.

Ingreso a la Plataforma

3 Acceso al Informe de Monitoreo Ambiental (IMA)

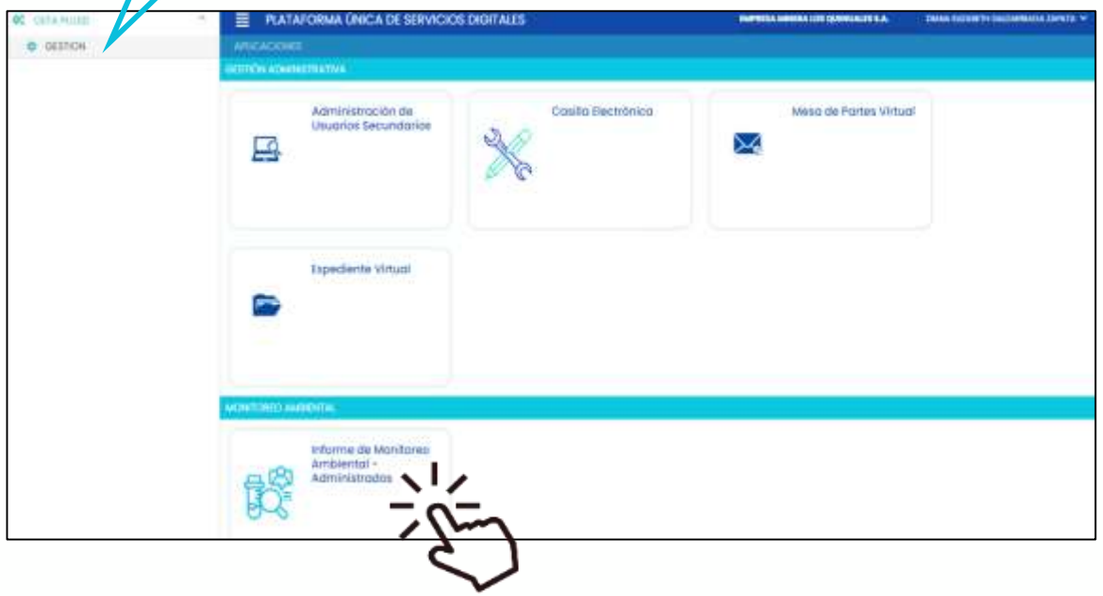

Acción del filtrar según los datos ingresados o seleccionados

Lista todos los registros de informes de monitoreo que pertenecen al administrado.

Permite agregar nuevos registros.

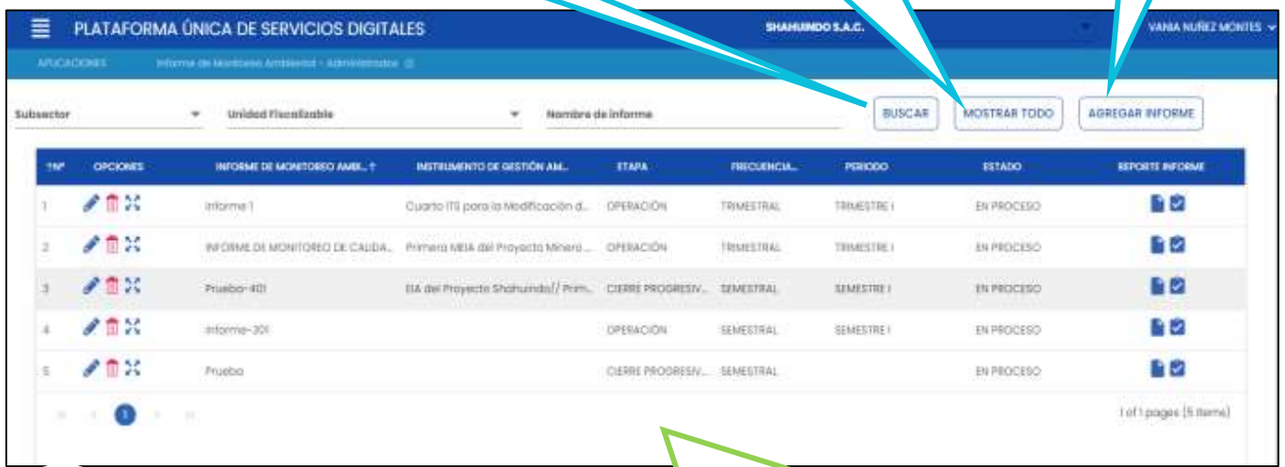

4 Panel de listado de Informes de Monitoreo Ambiental (IMA)

El usuario tiene la opción de seleccionar el Subsector y la Unidad Fiscalizable para listar los informes de monitoreo ambiental ingresados en la plataforma.

DOCUMENTO PRELIMINAR

Funcionalidades de la Plataforma

1 Registro del Informe de Monitoreo Ambiental (IMA)

Se pueden seleccionar varios Instrumentos de Gestión Ambiental

Aquí se ingresa datos generales como nombre, etapa, frecuencia de presentación de reporte, periodo de presentación de reporte e instrumentos de gestión ambiental relacionados a sus compromisos ambientales

2 Listado de Informes de Monitoreo registrados

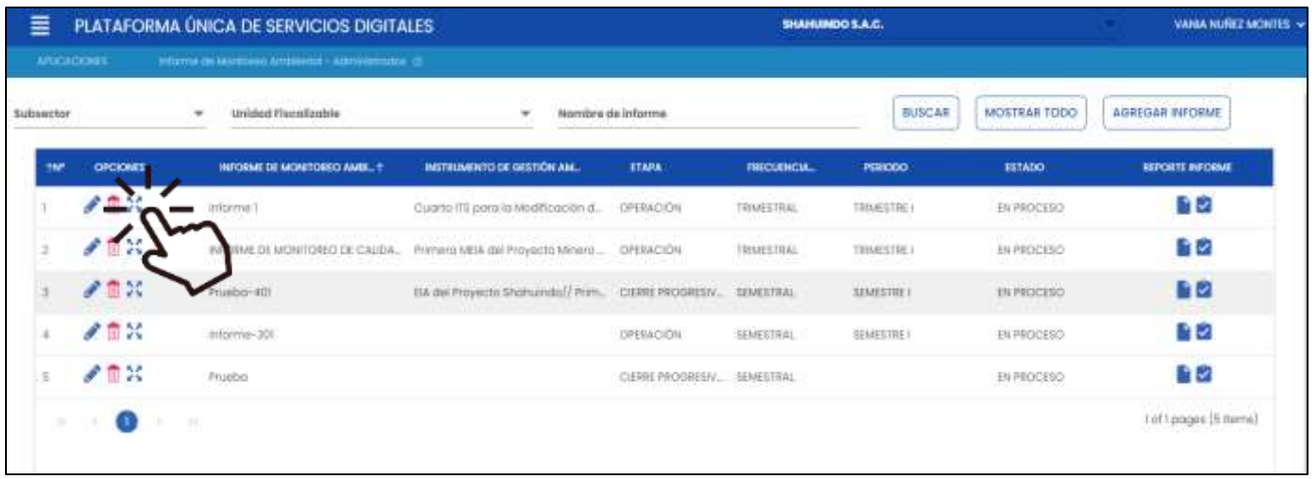

Editar

Mostrar Registro de Resultados.

Eliminar

DOCUMENTO PRELIMINAR

Funcionalidades de la Plataforma

3 Mostrar Registro de Resultados.

Luego de seleccionar el tercer icono “Mostrar registro de resultados”, se muestra la siguiente ventana.

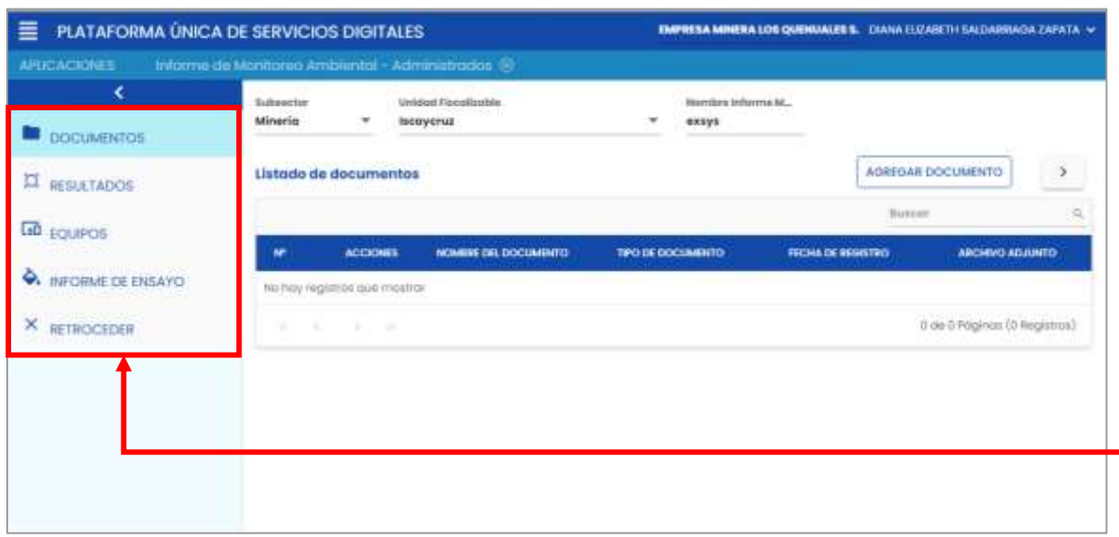

Muestra información de puntos de monitoreo asociados al IGA, sus componentes ambientales y parámetros.

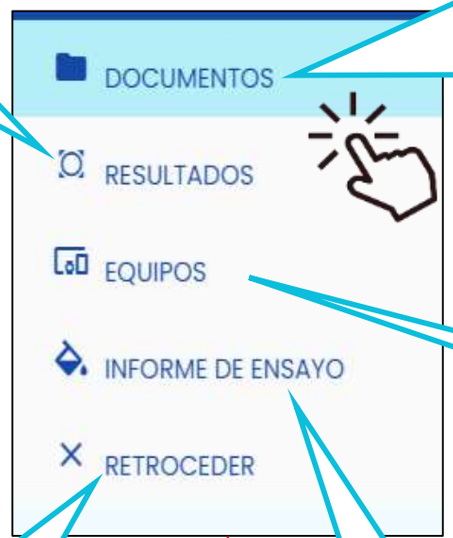

Muestra el listado de documentos como: cadena de custodia, certificado de calibración de laboratorio, informe de ensayo, datos de campo u otros.

Se registra información de equipos utilizados para la medición de parámetros.

Retrocede a la ventana de listado de informes.

Se registra los informes de ensayo proporcionados por el laboratorio con el listado de parámetros medidos

DOCUMENTO PRELIMINAR

Funcionalidades de la Plataforma

3.1 Registro de Documentos

Hacer click para agregar documentos

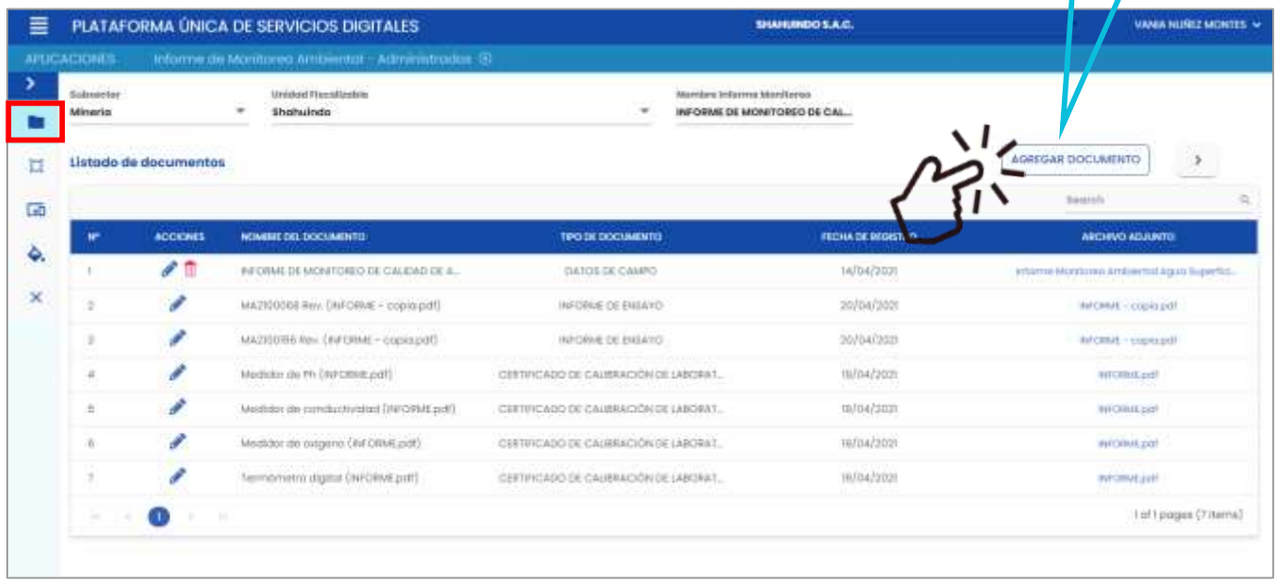

Dar click en Guardar

- Seleccionar el tipo de documento, ingresar el nombre y adjuntar el archivo.
- Permite adjuntar en formatos: .pdf,.docx,.doc,.zip,.rar y con un tamaño Máximo de 5GB.

Editar

Eliminar

NOTA:
Los documentos ingresados en las secciones de equipos e informe de ensayo se mostrarán en la sección de Documentos.

DOCUMENTO PRELIMINAR

Funcionalidades de la Plataforma

3.2 Resultados

Agrega información de puntos adicionales monitoreados para el informe

Selecciona puntos de monitoreo asociados al IGA registrado como parte del compromiso ambiental

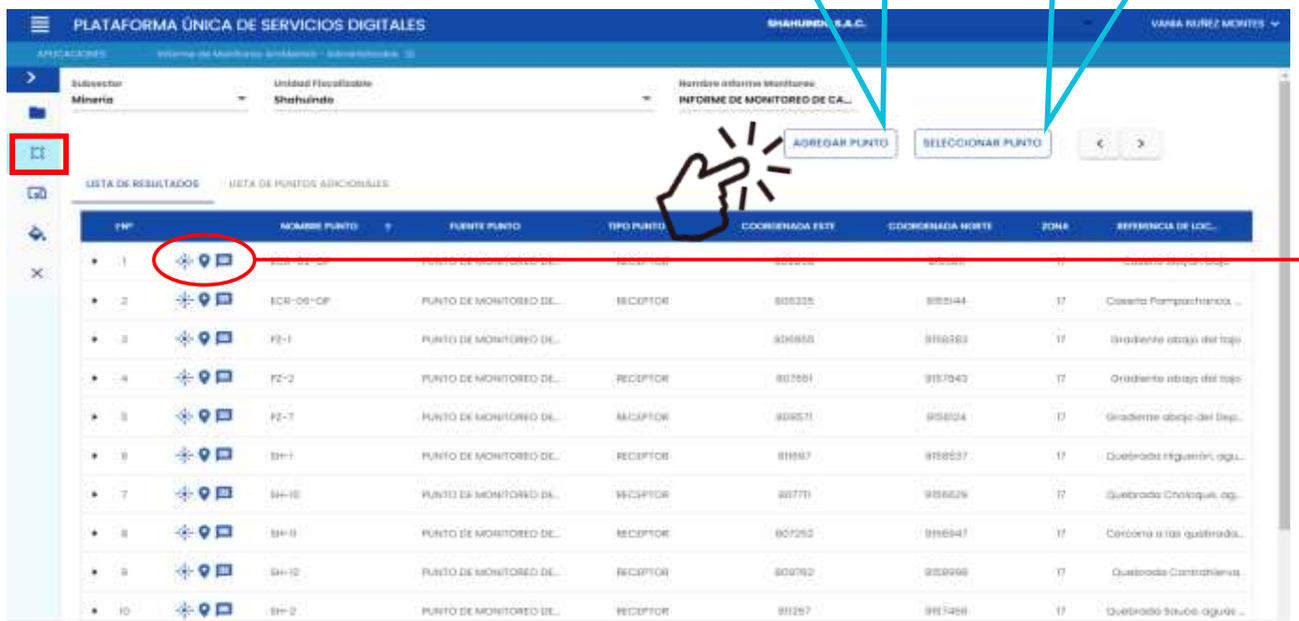

Muestra información de resultados de puntos de monitoreo asociados al IGA y puntos adicionales, con información de componentes ambientales, procedencia de la muestra y procedencia específica de la muestra.

Agregar Parámetros

Agregar coordenadas

Agregar observación

Agregar Parámetros: Selecciona los parámetros que pertenecen al punto de monitoreo desde un listado

Agregar Coordenadas: Se usa en el caso de ingresar y/o modificar datos de coordenadas.

Agregar Observación: Se usa para detallar algún cambio o actualización del punto de monitoreo.

DOCUMENTO PRELIMINAR

Funcionalidades de la Plataforma

Agregar Punto, únicamente se utiliza para crear Puntos Adicionales que por un mandato, norma o medida administrativa sea necesario incorporar en el informe.

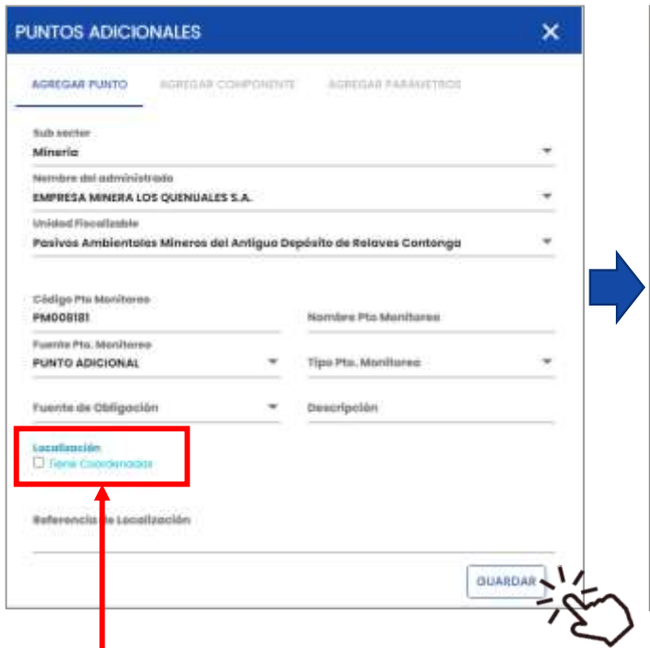

Los primeros campos muestran información por defecto. En los siguientes se registran Nombre Pto. Monitoreo, Tipo Pto. Monitoreo, Fuente de Obligación, Descripción, Localización (activar casilla) y Referencia de Localización. Clic en guardar.

Se despliega la información del Componente Ambiental, Procedencia de la muestra y Procedencia Específica de la Muestra y se da clic en la casilla empezando desde el ultimo nivel que corresponda al punto de monitoreo.

Se seleccionan los parámetros desde los desplegables de información de **Parámetros con Norma** o **Parámetros sin Norma**.

Luego dar clic en finalizar.

Se mostrará un aviso, dar clic en aceptar.

Nota: Antes de dar clic en Finalizar si se desea agregar otros datos de componentes ambientales y/o parámetros al mismo punto, se selecciona la pestaña a utilizar..

Funcionalidades de la Plataforma

Lista de Puntos Adicionales

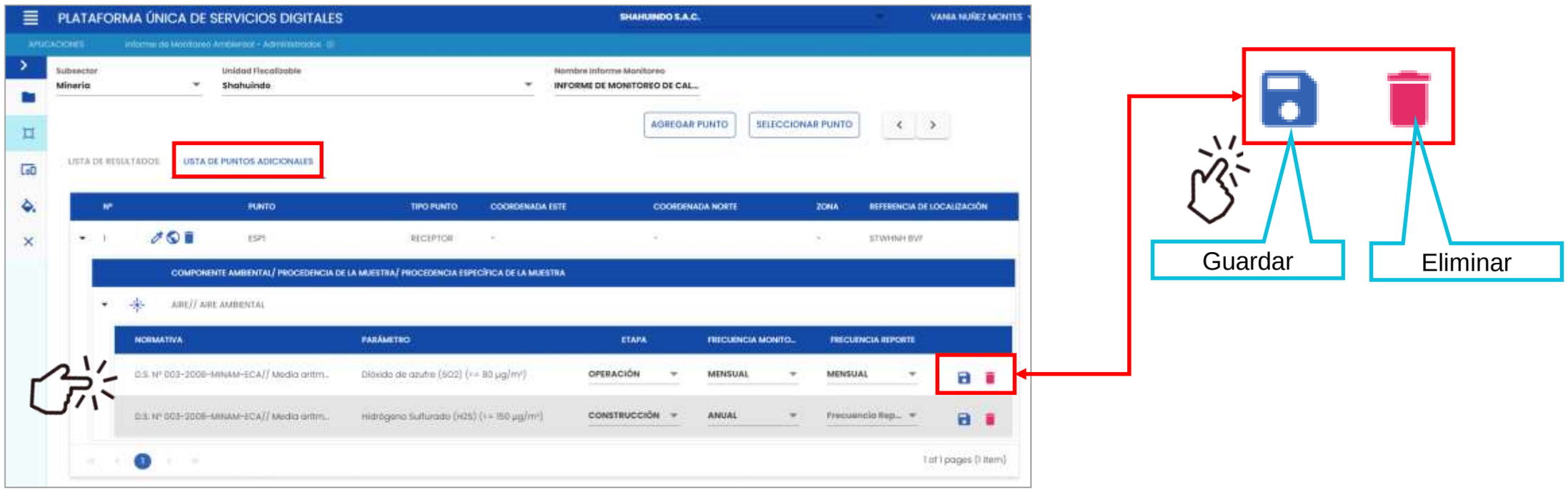

El administrado seleccionara información de: Etapa, Frecuencia de Monitoreo y Frecuencia del Reporte por cada parámetro en cada punto adicional incorporado.

Además. los valores de resultados de dichos parámetros se ingresaran desde la pestaña LISTA DE RESULTADOS

DOCUMENTO PRELIMINAR

Funcionalidades de la Plataforma

Permite seleccionar los puntos de los IGAs relacionados al informe de monitoreo ambiental de acuerdo a sus compromisos ambientales.

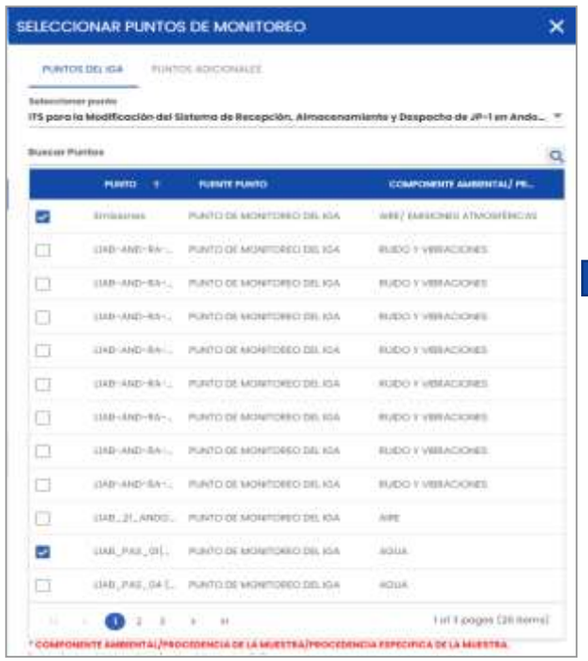

Para Puntos del IGA: Se selecciona marcando la casilla al (los) punto(s), de los que se ingresará información de resultados de monitoreo.

Para Puntos Adicionales: Se selecciona marcando la casilla al (los) punto(s) de los que se ingresará información de resultados de monitoreo.

Al terminar la selección se cierra la ventana dando clic en la X.

DOCUMENTO PRELIMINAR

Funcionalidades de la Plataforma

Lista de Resultados

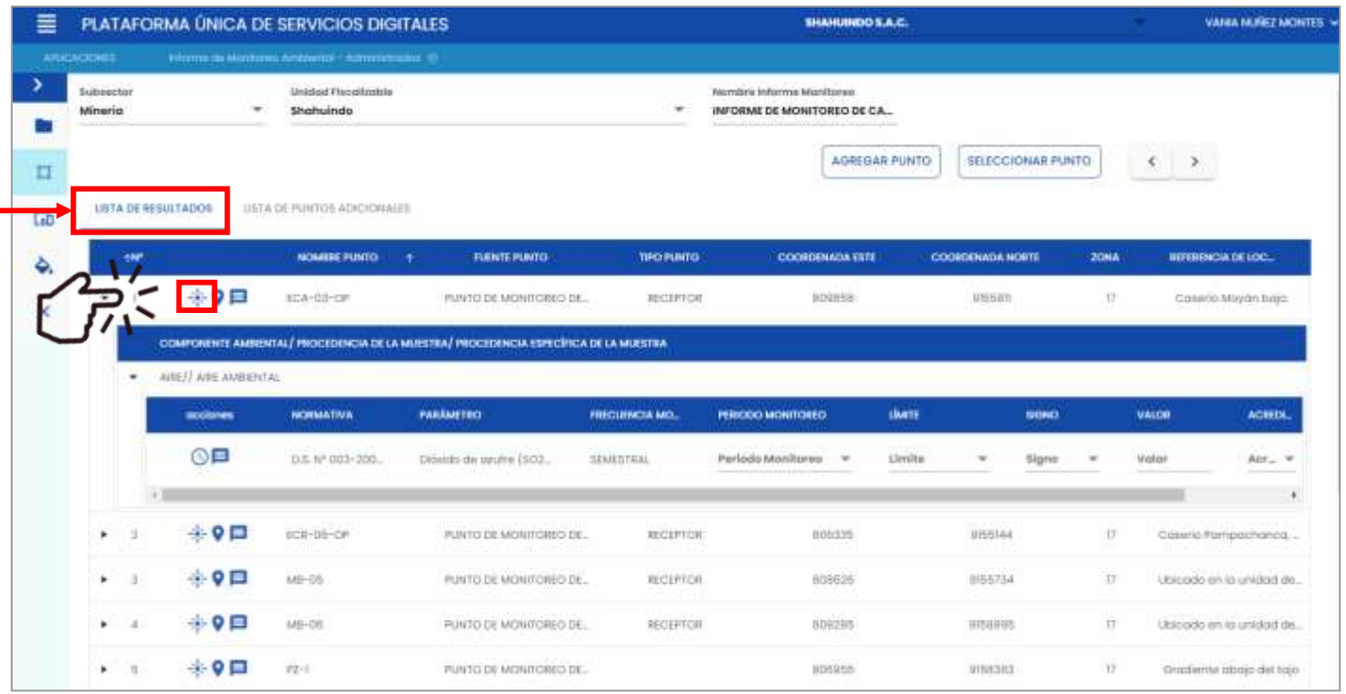

Lista de Resultados: Muestra el listado de puntos de monitoreo seleccionados a través de la herramienta SELECCIONAR PUNTO. En el cual se ingresara valores de parámetros.

Dar click en Agregar Parámetro

Al dar click en el componente ambiental se despliega la información de los parámetros asociados al punto del IGA.

En el caso de no tener parámetros asociados al punto del IGA dar click en MOSTRAR para desplegar la lista de parámetros adicionales y poder seleccionar desde la Lista de Parámetros con Norma y/o Parámetros sin Norma.

DOCUMENTO PRELIMINAR

Funcionalidades de la Plataforma

Lista de Resultados

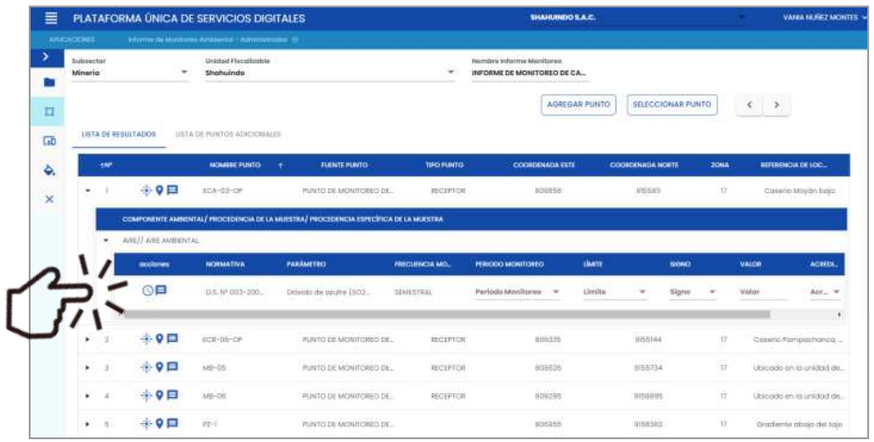

Agregar Muestra: Información de fecha y hora inicial y final y datos de envio.

Agregar Observación: Casilla para registrar información adicional respecto al parámetro del punto de monitoreo.

Muestra información asociada a lo parámetros seleccionados, excepto: Periodo de Monitoreo, Limite, Signo, Valor y Acreditación, que será ingresado de acuerdo a los resultados obtenidos del análisis de las muestras de campo y laboratorio.

DOCUMENTO PRELIMINAR

Funcionalidades de la Plataforma

3.3 Equipos

Muestra el listado de los equipos utilizados para la medición de los parámetros.

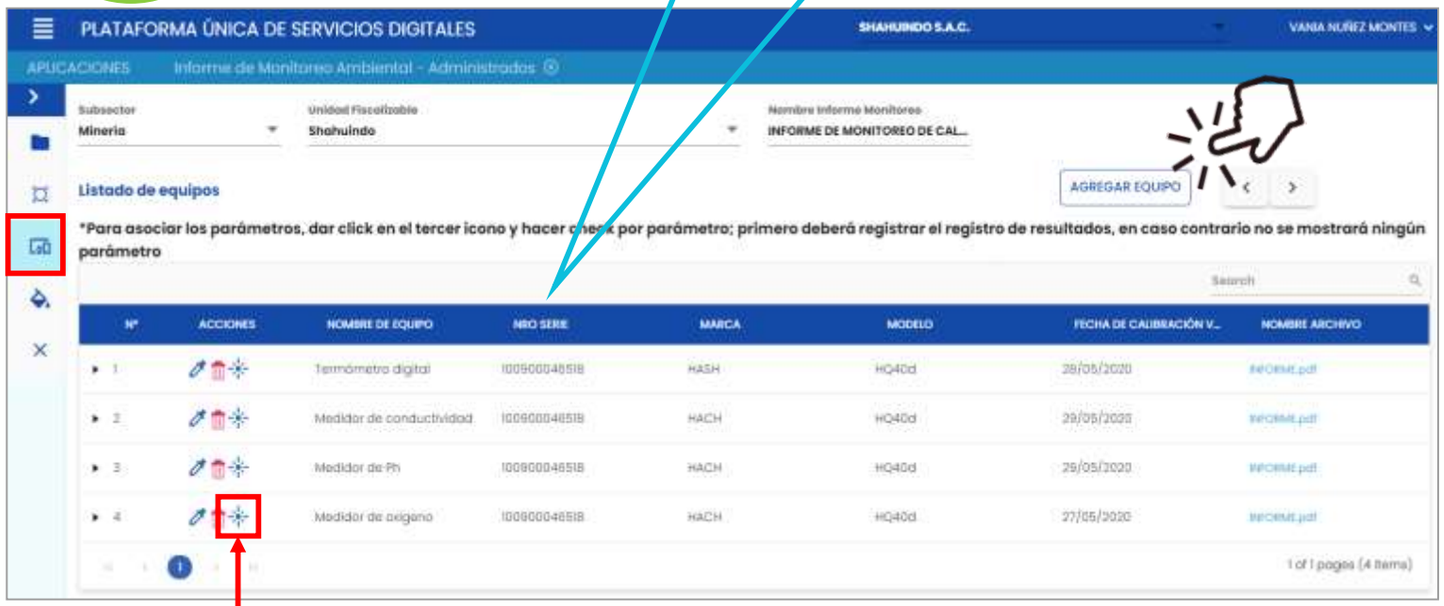

Información del equipo ambiental utilizado para la medición de los parámetros.

Permite adjuntar certificado de calibración en formatos: .pdf,.docx,.doc,.zip,.rar y con un tamaño Máximo de 5GB.

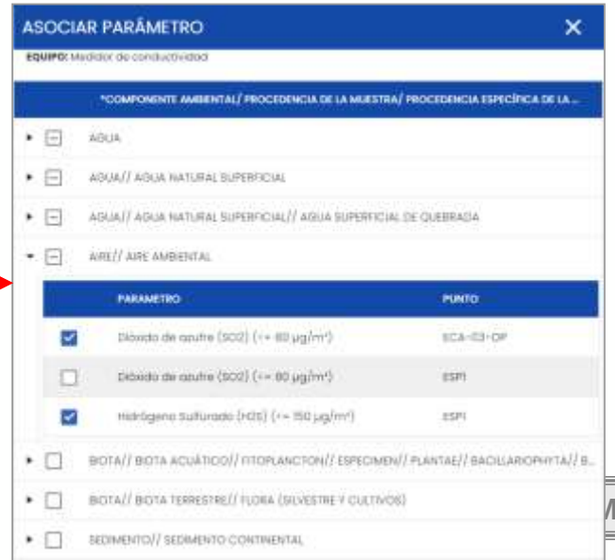

Con esta herramienta se asocia los parámetros medidos con el equipo ambiental utilizado en el monitoreo ambiental.

Los valores de resultados de estos parámetros se ingresarán en la pestaña LISTADO DE RESULTADOS.

Funcionalidades de la Plataforma

3.4 Informe de Ensayo

Muestra el listado de los Informes de Ensayo proporcionados por el laboratorio que realizo el análisis de la muestra.

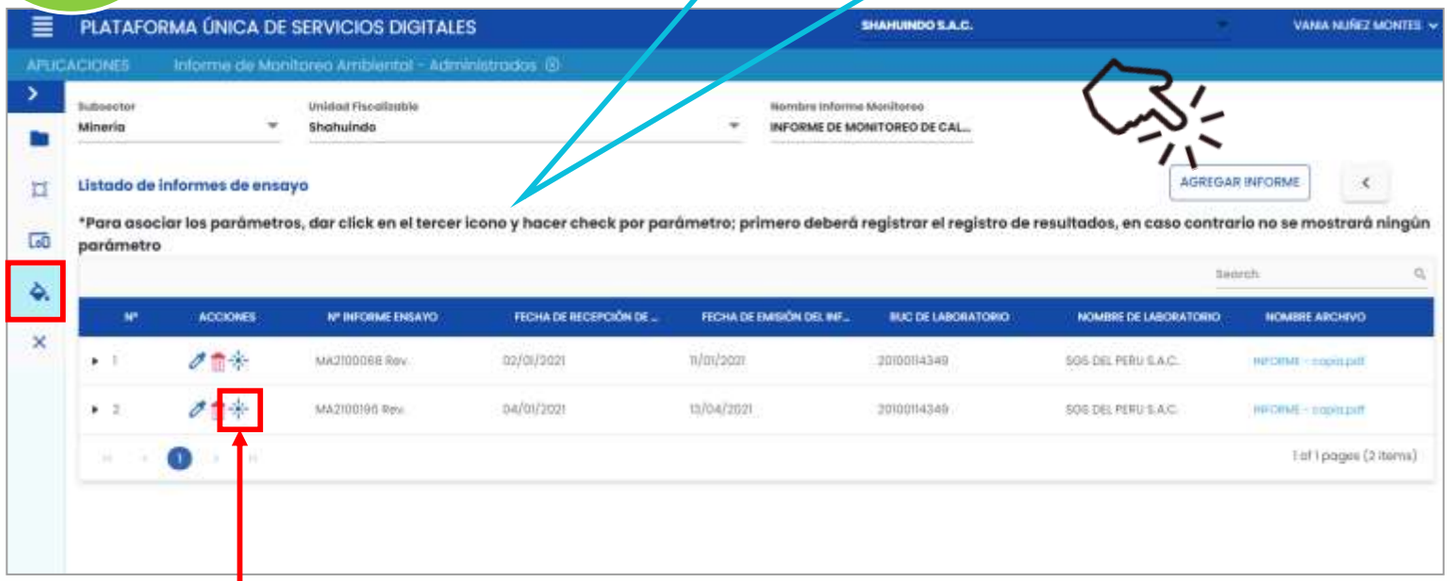

Información del Informe de Ensayo emitido por el laboratorio.

Permite adjuntar documentos relacionados al informe de ensayo en formatos: .pdf,.docx,.doc,.zip,.rar y con un tamaño máximo de 5GB.

Con esta herramienta se asocia los parámetros que se encuentran en el informe de ensayo emitido por el laboratorio después de haber realizado el análisis de la muestra en el monitoreo ambiental.

Los valores de resultados de estos parámetros se ingresarán en la pestaña LISTADO DE RESULTADOS.

MENTO PRELIMINAR

Funcionalidades de la Plataforma

4 Reporte de Informe de Monitoreo Ambiental

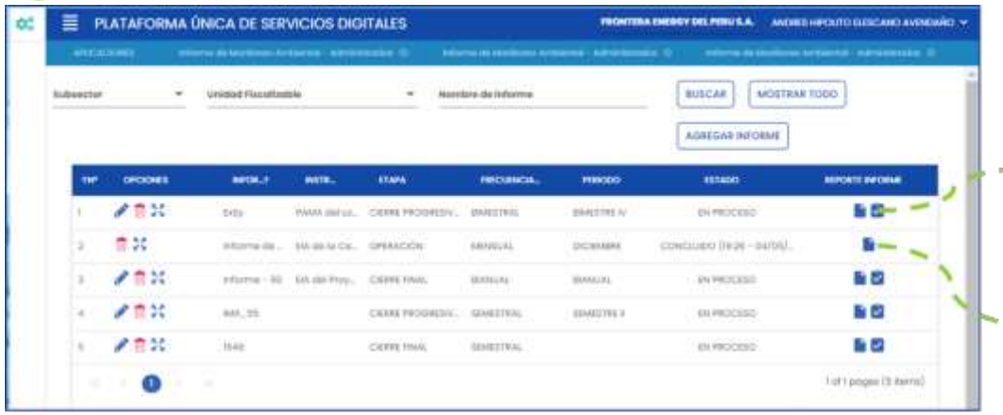

Al dar click muestra la visualización previa del reporte

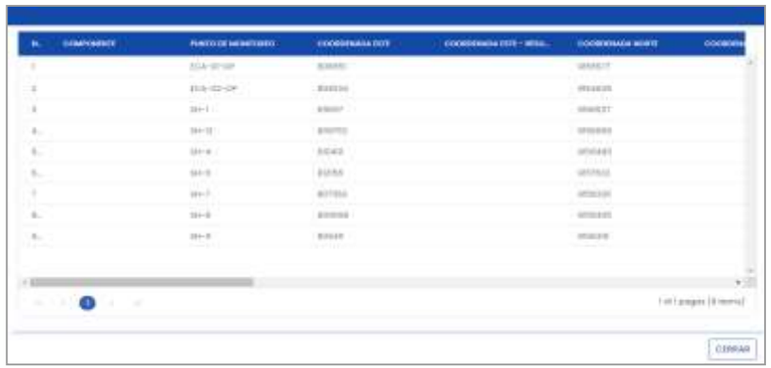

Al dar click en Concluir el Informe, el administrado puede generar su reporte de la información registrada en la plataforma en formato Excel.

Resultado-adminis....xlsx

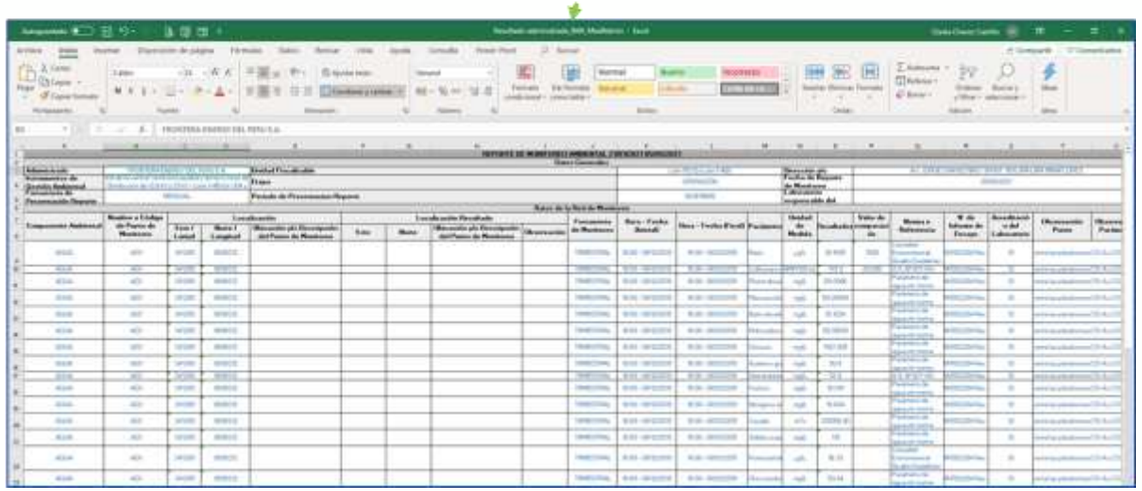

Nota: Una vez que se acepta Concluir el Informe, no hay opción a poder editar posteriormente los datos registrados.

Organismo
de Evaluación
y Fiscalización
Ambiental

Avenida Faustino Sánchez Carrión
N° 603, 607 y 615 - Jesús María
Tlf. 204-9900
www.oefa.gob.pe